Documentation

FFSSActus (RSS)

Projet : FFSSActus — Gestion et affichage de flux RSS

GitHub : https://github.com/Theo4500/FFSSActus

Sommaire

I. Structure de la base de données

II. Structure des fichiers

a. Arborescence du projet

b. Connexion à la base de données

c. CRUD des flux

1. Ajouter un flux

2. Afficher les flux

3. Modifier un flux

4. Supprimer un flux

d. Trier / Rechercher les flux

III. Affichage des flux RSS

a. Sections dynamiques

b. Sélection des flux

c. Résultat avec flux chargés

d. Proxy RSS

e. Persistance et rafraîchissement

f. Fichiers impliqués

IV. Carte Vigicrues

a. Présentation

b. Architecture technique

c. Fonctionnalités

d. Fichiers impliqués

I. Structure de la base de données

Nom de la base de données : ffssactus

Moteur : InnoDB — Interclassement : utf8mb4_bin

	Table	Action						Lignes	Type	Interclassement	Taille	Perte
☐	categorie		Parcourir	Structure	Rechercher	Insérer	Vider	Supprimer	3	InnoDB	utf8mb4_bin	16,0 kio	-
☐	flux		Parcourir	Structure	Rechercher	Insérer	Vider	Supprimer	6	InnoDB	utf8mb4_bin	32,0 kio	-
	2 tables	**Somme**							**9**	**InnoDB**	**utf8mb4_bin**	**48,0 kio**	**0 o**

Table : categorie

Colonne	Type	Contrainte	Description
`id_categorie`	INT	Clé primaire	Identifiant unique
`nom_categorie`	VARCHAR(50)	—	Nom de la catégorie

Table : flux

Colonne	Type	Contrainte	Description
`id_flux`	INT	Clé primaire	Identifiant unique du flux
`nom_flux`	VARCHAR(50)	—	Nom du flux RSS
`lien_flux`	VARCHAR(50)	—	URL du flux RSS
`id_categorie`	INT	Clé étrangère (NOT NULL)	Réf. vers categorie

II. Structure des fichiers

a. Arborescence du projet

```
FFSSActus/
├── index.php
├── connectbdd.php
├── ffssactusv2.sql
├── api/
│   ├── flux.php
│   └── proxy-rss.php
├── public/
│   ├── css/
│   │   └── style.css
│   ├── image/
│   │   └── logo-ffss_v2.jpeg
│   └── js/
│       ├── crudFlux.js
│       ├── loadFlux.js
│       ├── modalModif.js
│       ├── searchFlux.js
│       └── vigicrues.js
└── src/
    ├── add/
    │   └── addFlux.php
```

```
├── delete/
│   └── deleteFlux.php
├── read/
│   └── getFlux.php
├── update/
│   └── updateFlux.php
├── searchFlux.php
├── carte.php
├── page01.php
├── page02.php
├── page03.php
└── page04.php
```

b. Connexion à la base de données

Le fichier **connectbdd.php** établit la connexion PDO vers la base de données MySQL :

```
You, now | 1 author (You)
<?php
try {
    //Création de la connexion PDO
    $dns = 'mysql:host=192.168.1.239;dbname=ffssactus';
    $user = "root";

    $password = "rootroot";        You, now • Uncommitted changes
    $connexion = new PDO($dns, $user, $password);
    $connexion -> query("SET NAMES utf8");

} catch(Exception $e) {
    error_log("Erreur connexion BDD : " . $e->getMessage());
    echo "Erreur de connexion à la base de données. Veuillez réessayer plus tard.";
    exit;
}
?>
```

c. CRUD des flux

Les opérations CRUD permettent la gestion complète des flux RSS depuis l'interface d'administration.

Opération	Fichier PHP	Fichier JS	Description
Ajouter	`addFlux.php`	`crudFlux.js`	Formulaire d'ajout
Afficher	`getFlux.php`	`crudFlux.js`	Liste des flux
Modifier	`updateFlux.php`	`modalModif.js`	Modal d'édition
Supprimer	`deleteFlux.php`	`crudFlux.js`	Suppression avec confirmation

1. Ajouter un flux

L'ajout d'un flux se fait via le formulaire « Ajouter un flux » qui utilise les fichiers **addFlux.php** et **crudFlux.js**.

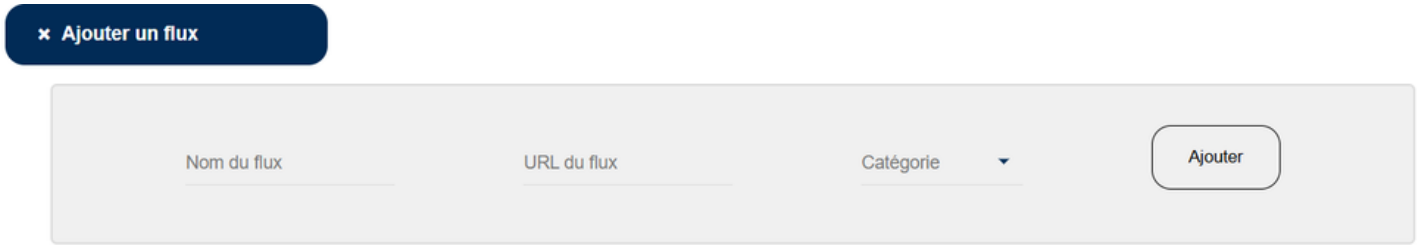

2. Afficher les flux

L'affichage des différents flux se fait grâce aux fichiers **getFlux.php** et **crudFlux.js**.

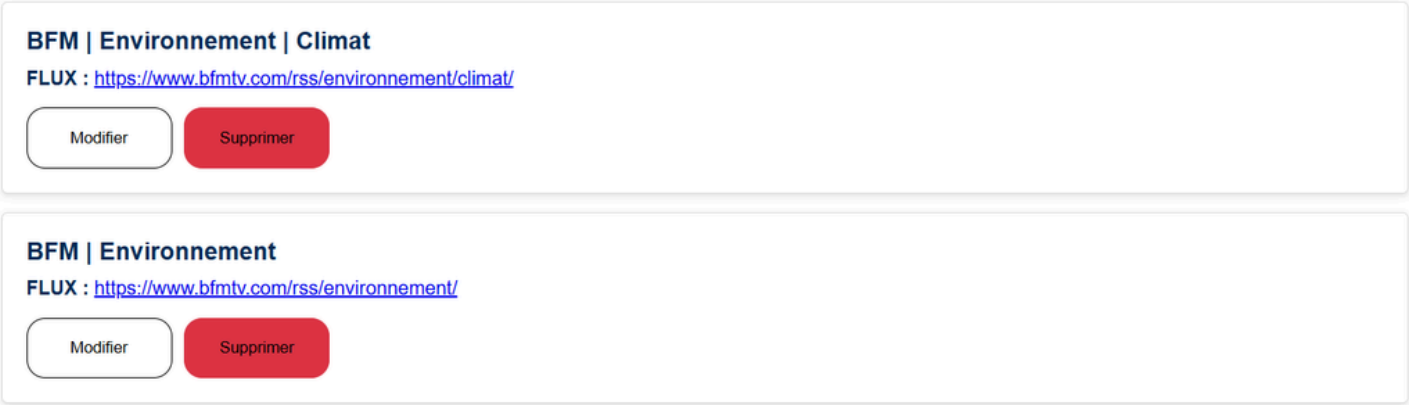

3. Modifier un flux

La modification d'un flux se fait via les fichiers **updateFlux.php** et **modalModif.js**.

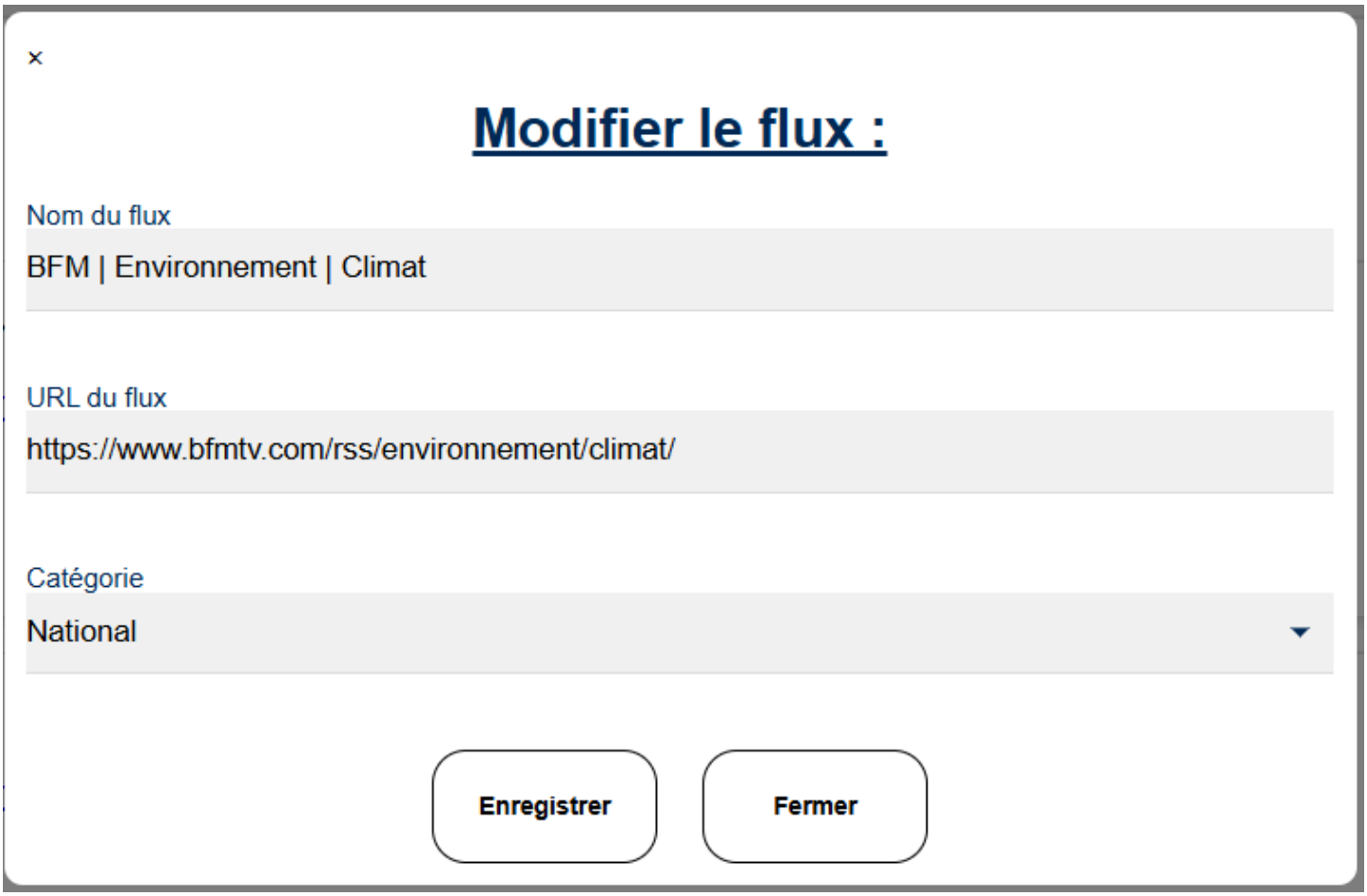

4. Supprimer un flux

La suppression de flux se fait avec les fichiers **deleteFlux.php** et **crudFlux.js**.

d. Trier / Rechercher les flux

Pour le tri ou la recherche de l'affichage de flux par nom ou catégorie, ceci utilise les fichiers **searchFlux.php** et **searchFlux.js**.

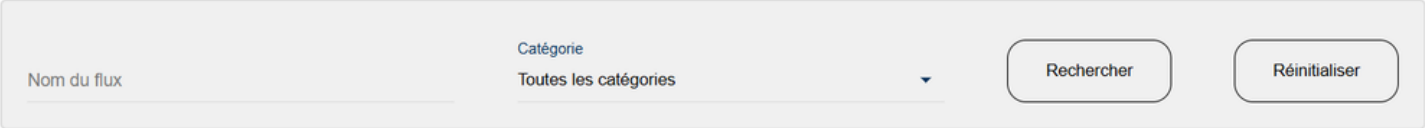

III. Affichage des flux RSS

Accès aux quatre pages d'affichage de flux via la navbar :

a. Sections dynamiques

Possibilité d'afficher un ou plusieurs flux avec les boutons d'ajout ou de suppression de section en haut de la page.

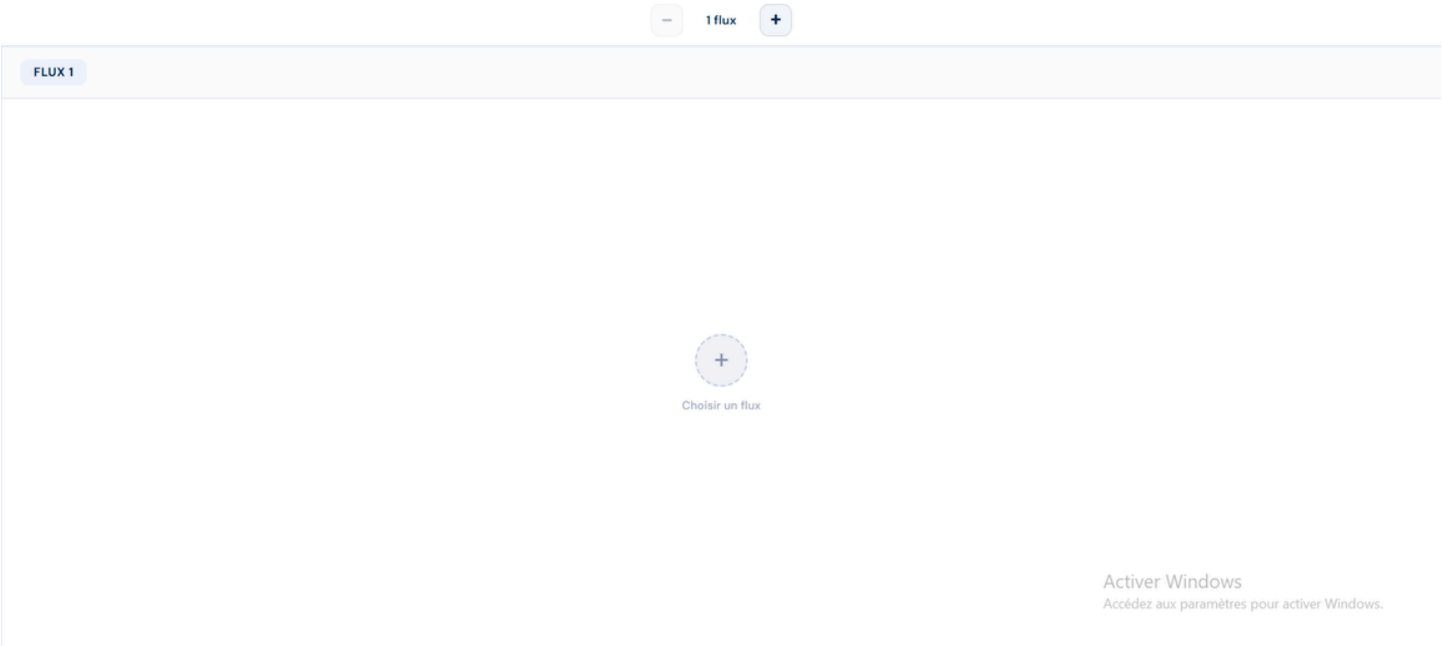

2 flux

FLUX 1

Choisir un flux

FLUX 2

Choisir un flux

Activer Windows
Accédez aux paramètres pour activer Windows.

3 flux

FLUX 1

Choisir un flux

FLUX 2

Choisir un flux

FLUX 3

Choisir un flux

Activer Windows
Accédez aux paramètres pour activer Windows.

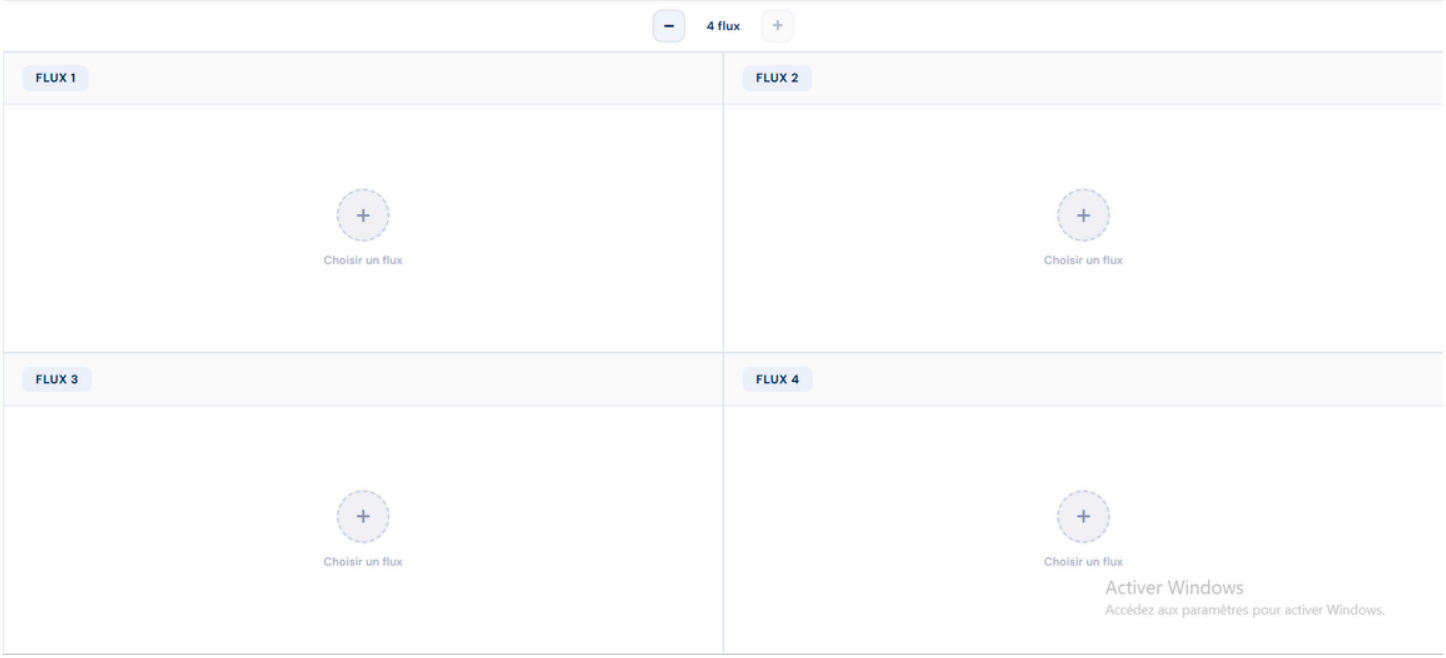
4 flux
FLUX 1
Choisir un flux
FLUX 2
Choisir un flux
FLUX 3
Choisir un flux
FLUX 4
Choisir un flux
Activer Windows
Accédez aux paramètres pour activer Windows.

b. Sélection des flux

Ajout d'un flux via le bouton « Choisir un flux » :

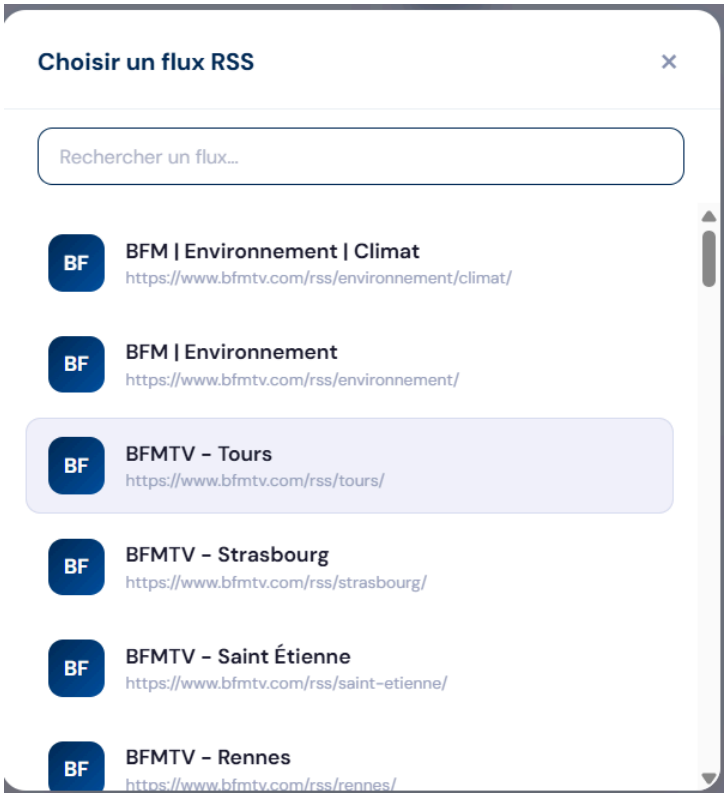

c. Résultat avec flux chargés

Les articles de chaque flux s'affichent dans les sections correspondantes :

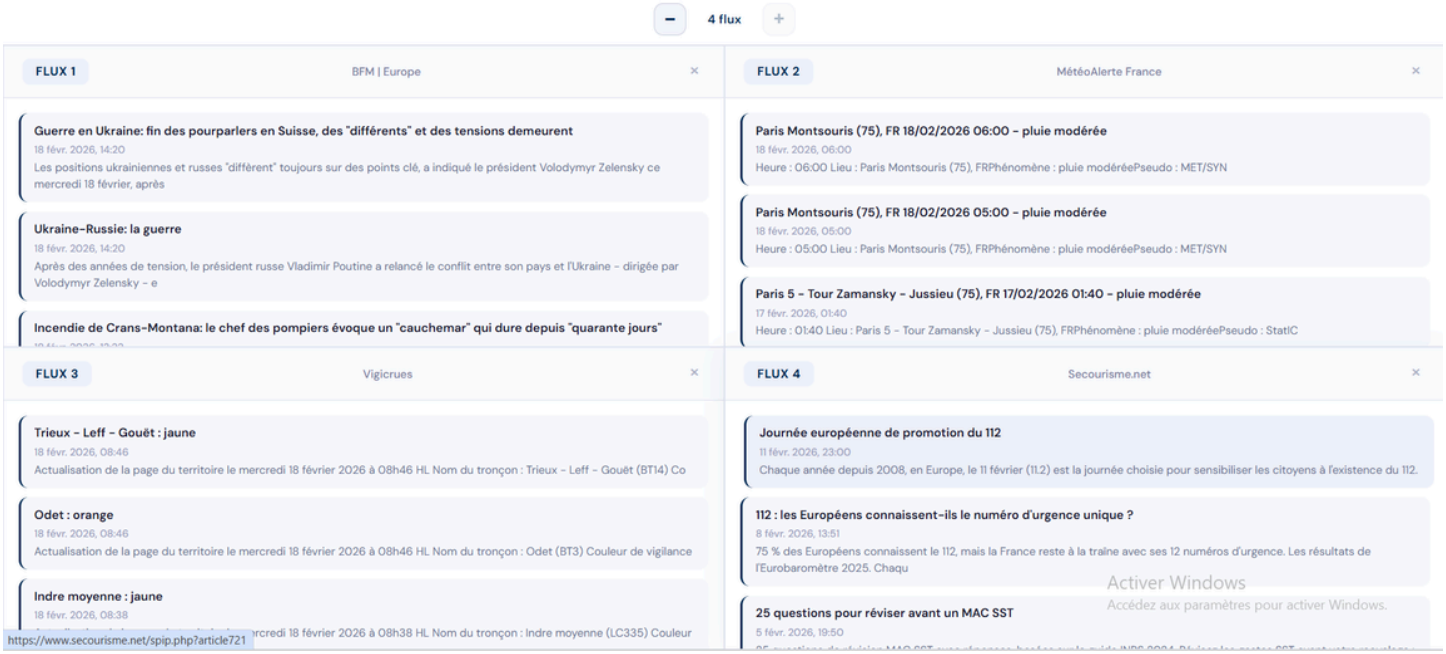

d. Proxy RSS

Le fichier **proxy-rss.php** sert de proxy côté serveur pour contourner les restrictions CORS. Il récupère le contenu RSS via cURL et le retourne au format JSON.

e. Persistance et rafraîchissement

Les sélections de flux et le nombre de sections sont sauvegardés dans le localStorage du navigateur avec des clés uniques par page. Les flux se rechargent automatiquement **toutes les minutes**.

f. Fichiers impliqués

Fichier	Rôle
`src/page01-04.php`	Pages d'affichage des flux RSS
`public/js/loadFlux.js`	Sections, sélection, parsing RSS, persistance, auto-refresh
`api/proxy-rss.php`	Proxy serveur CORS
`public/css/style.css`	Styles grille, sections, modal et responsive

IV. Carte Vigicrues

a. Présentation

La page **carte.php** affiche une carte interactive plein écran des vigilances crues en France, alimentée par les données officielles de Vigicrues (vigicrues.gouv.fr). La carte utilise **Leaflet.js** avec un fond **OpenStreetMap** et affiche les 337 tronçons de cours d'eau surveillés, colorés selon leur niveau d'alerte. (**Utilisation de l'API du site Vigicrues**)

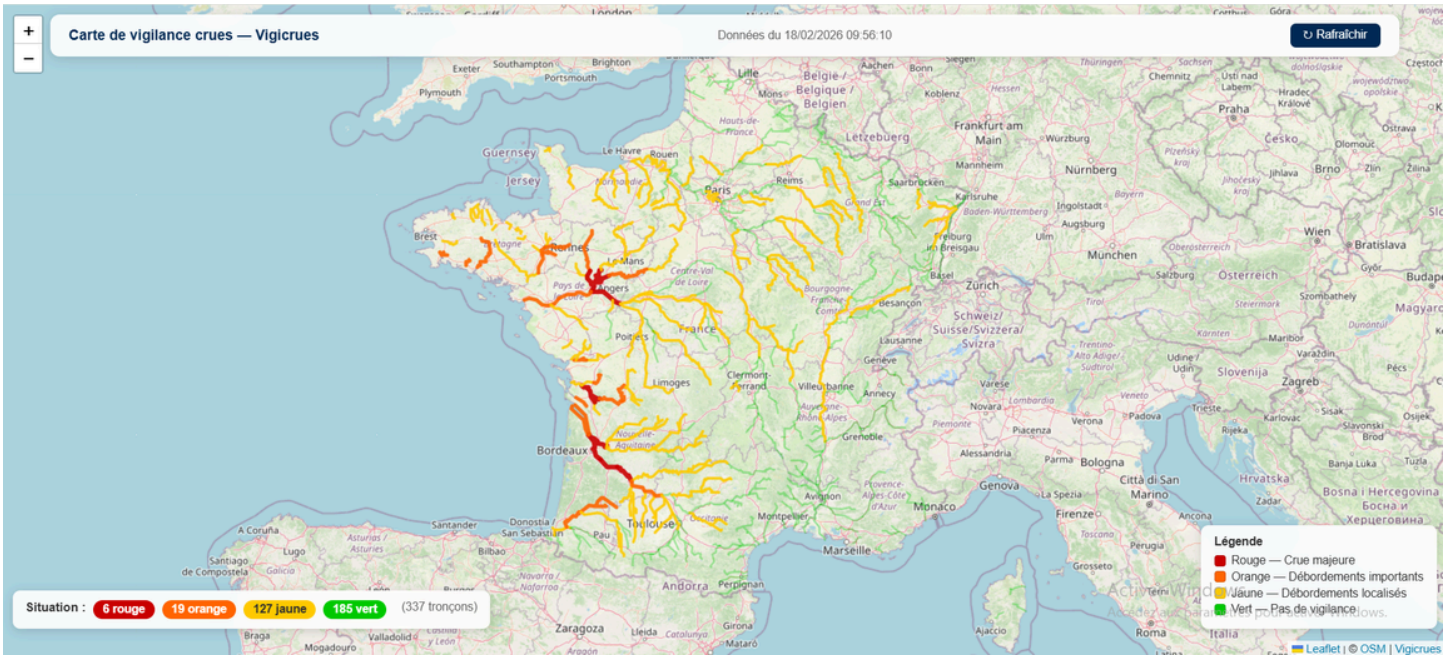

Les quatre niveaux de vigilance sont :

Niveau	Couleur	Code	Signification
1	**Vert**	`#00cc00`	Pas de vigilance particulière requise
2	**Jaune**	`#ffcc00`	Risque de débordements localisés
3	**Orange**	`#ff6600`	Risque de débordements importants
4	**Rouge**	`#cc0000`	Risque de crue majeure

b. Architecture technique

Les données proviennent de **l'API GeoJSON** officielle de Vigicrues :

https://www.vigicrues.gouv.fr/services/1/InfoVigiCru.geojson

Le flux de données suit ce parcours :

API Vigicrues	→ proxy-rss.php	→ fetch JS	→ parse GeoJSON	→ **Leaflet**

Le proxy est nécessaire car le navigateur ne peut pas appeler directement l'API Vigicrues (restriction CORS). Le GeoJSON retourné contient des features avec les propriétés suivantes :

Propriété	Description
`NivInfViCr`	Niveau de vigilance (1 à 4)
`lbentcru`	Nom du tronçon (ex: "Loire orléanaise")
`CdEntCru`	Code du tronçon
`CdTCC`	Code du territoire de compétence

c. Fonctionnalités

Interface carte plein écran

La carte occupe 100% de la fenêtre du navigateur. Les éléments d'interface sont en overlay flottant :

— Barre supérieure : titre, date de mise à jour, bouton rafraîchir

— Légende : en bas à droite, couleurs des 4 niveaux

— Statistiques : en bas à gauche, nombre de tronçons par niveau

Interaction avec les tronçons

Chaque tronçon de cours d'eau est cliquable et affiche une popup contenant le nom du cours d'eau, le niveau d'alerte (badge coloré), les codes tronçon et territoire, et un lien vers le site Vigicrues. Au survol, les lignes s'épaississent pour faciliter la sélection.

Rafraîchissement automatique

Les données se rechargent automatiquement toutes les minutes pour maintenir la carte à jour. Un bouton de rafraîchissement manuel est également disponible.

Conversion de coordonnées

Le code inclut une fonction de conversion Lambert 93 (EPSG:2154) vers WGS84 en cas de besoin, bien que les données actuelles soient déjà en WGS84.

d. Fichiers impliqués

Fichier	Rôle
`src/carte.php`	Page HTML de la carte (structure, overlays)
`public/js/vigicrues.js`	Logique JS : fetch, rendu Leaflet, stats, auto-refresh
`api/proxy-rss.php`	Proxy CORS (partagé avec les flux RSS)
`public/css/style.css`	Styles carte : overlays, popups, légende, responsive

Dépendances externes

Bibliothèque	Usage
Leaflet.js 1.9.4	Affichage de la carte interactive et des couches GeoJSON
OpenStreetMap	Tuiles de fond de carte (fond cartographique)